WIKIPEDIA
Ensiklopedia Bebas

Monako

Monako /ˈmɒnəkoʊ/ simak, secara resmi **Kepangeranan Monako** (bahasa Prancis: *Principauté de Monaco* (pengucapan bahasa Prancis: [prɛ̃.si.po.te.d(ə).mɔ.na'ko]), Monégasque: *Prinçipatu de Mùnegu*, bahasa Liguria: *Prinçipato de Mónego*, bahasa Italia: *Principato di Monaco*, bahasa Oksitan: *Principat de Mónegue*) adalah sebuah negara kota berdaulat, yang terletak di Côte d'Azur di Eropa Barat. Berbatasan dengan Prancis di tiga sisi, dan satu sisi berbatasan dengan Laut Tengah, pusatnya adalah sekitar 16 km (9,9 mi) dari Italia, dan hanya 13 km (8,1 mi) dari timur laut Nice, Prancis.[7] Monako mempunyai luas wilayah 2,02 km² dan populasi sebesar 37.550 (2016),[8] hal ini membuat Monako menjadi negara kedua terkecil dan paling padat penduduk di dunia.[9] Monako mempunyai perbatasan darat hanya 4,4 km (2,7 mi), dan garis pantai 4,1 km (2,5 mi), dan lebar yang bervariasi antara 1,7 km (1,1 mi), dan 349 meter (382 yard).[10][11] Titik tertinggi dari negara ini adalah jalur sempit yang bernama Chemin des Révoires di lereng gunung Mont Agel, di distrik Les Révoires, yang tingginya 161 meter (528 feet) di atas permukaan laut.[12] *Quartier* terpadat di Monako adalah Monte Carlo, dan *Ward* terpadat adalah Larvotto/Bas Moulins.[13] Monaco terkenal dengan reklamasi tanahnya, yang telah meningkat ukurannya sekitar 20%. Proyek reklamasi tanah yang sekarang meliputi, memperluas distrik Fontvieille sekitar 008 km² (3,1 sq mi) atau 8 ha (19.8 akre).[14][15][16][17][18]

Monako adalah sebuah kepangeranan yang diatur dalam monarki konstitusional, dengan Pangeran Albert II sebagai kepala negara.[19] Meskipun Pangeran Albert II adalah raja konstitutional, ia masih punya kekuatan politik yang sangat besar.[20] Rumah Grimaldi telah memerintah Monako, dengan interupsi singkat, sejak 1297.[21] Bahasa resminya adalah Prancis, tetapi Monégasque, Italia, dan Inggris banyak dituturkan dan dimengerti secara luas.[note 1] Kedaulatan negara secara resmi diakui dalam Perjanjian Franco-Monegasque (1861), dengan Monako menjadi anggota voting penuh PBB pada tahun 1993, setelah banyak perdebatan politik.[9] Meskipun kemerdekaan Monaco dan kebijakan luar negeri yang terpisah, pertahanan adalah tanggung jawab Prancis.[22] Meskipun demikian, Monako tetap mempertahakan dua unit militer, berjumlah 263 orang, *Corps des Sapeurs-Pompiers*, dan *Compagnie des Carabiniers du Prince*.[23][24]

Pembangunan ekonomi Monako didorong pada akhir abad ke-19 dengan kereta api menuju Prancis, dan pembukaan kasino pertama, Monte Carlo.[25] Sejak itu, iklim yang nyaman, pemandangan yang indah, dan fasilitas perjudian telah membuat Monako terkenal di dunia sebagai wisata, dan pusat rekreasi untuk orang kaya dan terkenal.[11][26] Namun, dalam beberapa tahun terakhir Monako telah menjadi pusat perbankan utama yang memegang lebih dari dana senilai €100 miliar,[27] dan telah berhasil berupaya untuk mendiversifikasi ekonominya ke Layanan dan kecil, nilai tambah tinggi, dan industri non-polusi.[28]

Kepangeranan Monako
Principauté de Monaco (Prancis)

Bendera

Lambang

Semboyan: Deo Juvante
(Indonesia: "Dengan Bantuan Tuhan")

Lagu kebangsaan: L'hymne Monégasque
(Indonesia: Himne Monako)

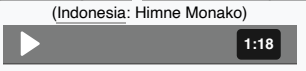

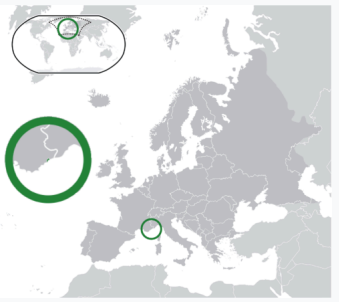

Ibu kota	Kota Monako 43°43′N 7°25′E
Quartier	Monte Carlo 43°44′23″N 7°25′38″E
Bahasa resmi	Prancis
Pemerintahan	Monarki semi-konstitusional[1]
• Pangeran	Albert II
• Menteri Negara	Pierre Dartout
Legislatif	Conseil National
Kemerdekaan	
• Dinasti Grimaldi	1297
• Perjanjian Prancis-Monako	1861
Luas	
- Total	2,02 km² (248)
- Perairan (%)	dapat diabaikan
Populasi	
- Perkiraan 2019	— 38.300[1] (190)
- Sensus Penduduk 2016	37.308[2]
- Kepadatan	18.713/km² (1)
PDB (KKB)	2015
- Total	▲ $7,672 miliar[3] (168)
- Per kapita	▲ $115.700[3] (3)
PDB (nominal)	2019[b]
- Total	▲ $7,424 miliar[4] (159)
- Per kapita	▲ $190.513[5] (2)
IPM (2012)	0,964[6] sangat tinggi · 1
Mata uang	Euro (€) (EUR)
Zona waktu	Waktu Eropa Tengah (CET) (UTC+1)
- Musim panas (DST)	UTC+2 (Waktu Musim Panas Eropa Tengah (CEST))
Lajur kemudi	kanan
Kode telepon	+377
Kode ISO 3166	MC
Ranah Internet	.mc

1. Dalam sistem monarki semi-konstitusional, perdana menteri adalah pemegang kekuasaan eksekutif pada pemerintahan; namun raja masih memiliki kekuatan politik yang cukup besar untuk melaksanakan kebijakannya sendiri.

lihat · bicara · sunting (https://id.wikipedia.org/w/index.php?title=Templat:Monako_infobox&action=edit)

Sejarah

Artikel utama: Sejarah Monako



Istana Pangeran di Monaco-Ville.

Katedral Santo Nicholas di Monaco-Ville.

Place d'Armes di La Condamine.

Nama Monako datang dari sekitar abad ke-6 SM koloni Yunani Phokaia. Mengacu dari bahasa Liguria *Monoikos*, dari bahasa Yunani "μόνοικος", "satu rumah", dari "μόνος" (*monos*) "sendiri" [29] + "οἶκος" (*oikos*) "rumah",[30] yang menanggung rasa orang-orang baik menetap di "satu tempat tinggal" atau "hidup terpisah" dari orang lain. Menurut mitos kuno, Hercules melewati daerah Monako dan mengusir para dewa sebelumnya.[31] Hasilnya, sebuah kuil dibangun di sana, kuil Herkules Monoikos. Karena satu-satunya candi di daerah ini adalah "Rumah" Hercules, kota ini disebut Monoikos.[32][33]

Setelah penghibahan tanah dari Kaisar Henry VI pada 1191, Monako didirikan kembali pada tahun 1215 sebagai koloni Genoa.[34][35] Monaco pertama kali diperintah oleh Rumah Grimaldi pada tahun 1297, ketika Francesco Grimaldi, yang dikenal sebagai "*Il Malizia*" (diterjemahkan dari bahasa Italia baik sebagai "si berbahaya" atau "si licik"), dan anak buahnya menangkap benteng melindungi Batu Monako dan berpakaian sebagai biarawan Fransiskan- sebuah *Monako* dalam bahasa Italia, meskipun ini adalah kebetulan karena daerah tersebut sudah dikenal dengan nama ini.[36]

Pada 1419, Grimaldi membeli Monako dari mahkota Aragon dan menjadi penguasa resmi dan tak terbantahkan dari "Batu Monako", dan pada tahun 1612 Honore II mulai menggelari dirinya sebagai "Pangeran" dari Monako.[37]

Geografi

Artikel utama: Geografi Monako
Lihat pula: Reklamasi tanah di Monako

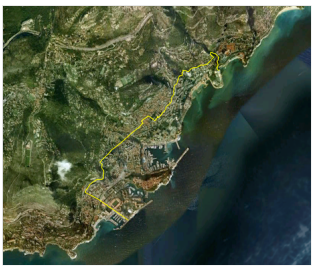

Citra satelit Monako, dengan perbatasan Monegasque-Prancis terlihat dalam warna kuning.

Monako adalah sebuah negara-kota yang berdaulat, dengan 5 *quartier* dan 10 *ward*,[38] terletak di Côte d'Azur di Eropa Barat. Berbatasan dengan Prancis di tiga sisi, dan satu sisi berbatasan dengan Laut Tengah, pusatnya adalah sekitar 16 km (9,9 mi) dari Italia, dan hanya 13 km (8,1 mi) dari timur laut Nice, Prancis.[7] Monako mempunyai luas wilayah 2,02 km² dan populasi sebesar 37.550 (2016),[8] hal ini membuat Monako menjadi negara kedua terkecil dan paling padat penduduk di dunia. Monako mempunyai perbatasan darat hanya 44 km (27 mi), dan garis pantai 41 km (25 mi), dan lebar yang bervariasi antara 17 km (11 mi), dan 349 meter (382 yard).

Titik tertinggi dari negara ini adalah jalur sempit yang bernama Chemin des Révoires di lereng gunung Mont Agel, di distrik Les Révoires, yang tingginya 161 meter (528 feet) di bawah permukaan laut.[12] Titik terendah dari negara ini adalah Laut Tengah yang berada di permukaan laut.[39][40]

Iklim

Data iklim Monaco [semb

Bulan	Jan	Feb	Mar	Apr	Mei	Jun	Jul	Agt	Sep	Okt	Nov	Des	Ta
Rata-rata tertinggi °C (°F)	12.3 (54.1)	12.5 (54.5)	14.0 (57.2)	16.1 (61)	19.4 (66.9)	23.0 (73.4)	25.8 (78.4)	25.9 (78.6)	23.8 (74.8)	19.9 (67.8)	16.1 (61)	13.4 (56.1)	1 (6
Rata-rata harian °C (°F)	10.2 (50.4)	10.4 (50.7)	11.8 (53.2)	13.9 (57)	17.1 (62.8)	20.8 (69.4)	23.5 (74.3)	23.7 (74.7)	21.6 (70.9)	17.8 (64)	14.0 (57.2)	11.4 (52.5)	1 (6
Rata-rata terendah °C (°F)	8.1 (46.6)	8.2 (46.8)	9.6 (49.3)	11.6 (52.9)	14.8 (58.6)	18.5 (65.3)	21.2 (70.2)	21.5 (70.7)	19.3 (66.7)	15.6 (60.1)	11.9 (53.4)	9.3 (48.7)	1 (5
Presipitasi mm (inci)	82.7 (3.256)	76.4 (3.008)	70.5 (2.776)	62.2 (2.449)	48.6 (1.913)	36.9 (1.453)	15.6 (0.614)	31.3 (1.232)	54.4 (2.142)	108.2 (4.26)	104.2 (4.102)	77.5 (3.051)	76 (30
Rata-rata hari hujan atau bersalju	6.8	6.4	6.1	6.3	5.2	4.1	1.9	3.1	4.0	5.8	7.0	6.0	6
Rata-rata sinar matahari bulanan	148.8	152.6	201.5	228.0	269.7	297.0	341.0	306.9	240.0	204.6	156.0	142.6	2.6

Sumber: Situs web Monako[41]

Politik

Artikel utama: Politik Monako

Monako telah diatur di bawah monarki konstitusional sejak tahun 1911, dengan Pangeran Monako sebagai kepala negara. Badan eksekutif terdiri dari Menteri Negara sebagai kepala pemerintahan, yang memimpin lima anggota dewan pemerintahan.[42] Hingga 2002, menteri negara adalah warga negara Prancis yang ditunjuk oleh pangeran dari calon yang diajukan oleh pemerintah Prancis, sejak amendemen konstitusi tahun 2002, menteri negara dapat berupa orang Prancis ataupun Monegasque[34] Namun, pada tanggal 3 Maret 2010, Pangeran Albert II mengangkat seorang Prancis bernama Michel Roger sebagai menteri negara.[43]

Berdasarkan konstitusi 1962, pangeran berbagi hak vetonya dengan Dewan Nasional.[44] 24 anggota dewan nasional dipilih untuk masa jabatan lima tahun; 16 yang dipilih melalui sistem pemilihan mayoritas dan 8 oleh perwakilan proporsional.[45] Semua undang-undang memerlukan persetujuan dari dewan nasional, yang saat ini didominasi oleh Uni Monako (UPM), yang berpusat-kanan yang memegang dua puluh satu kursi.[45] Satu-satunya partai lain yang diwakili di dewan nasional adalah Reli dan Isu untuk Monako (REM), yang bersayap-kanan yang memegang hanya tiga kursi.[45] Urusan kota Monako diarahkan oleh Dewan Komunal,[46] yang terdiri dari empat belas anggota yang dipilih dan dipimpin oleh wali kota.[47] Berbeda dengan Dewan Nasional, anggota dewan yang dipilih untuk masa empat tahun,[48] adalah non-partisan secara ketat, bagaimanapun, oposisi di dalam dewan sering dibentuk.[46][49]

Pembagian administratif

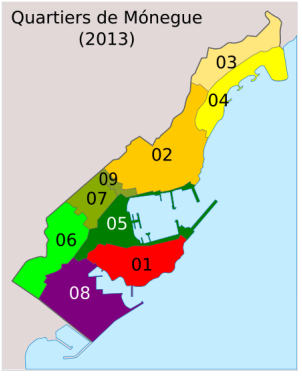

Ward Monako.

Monako adalah negara kedua terkecil di dunia (berdasarkan ukuran) di dunia; hanya Vatikan yang lebih kecil.[50] Monako juga merupakan negara monarki kedua terkecil di dunia[51] dan paling padat di dunia.[52] Monako hanya memiliki satu munisipalitas.[53] Tidak ada perbedaan geografis antara negara dan kota Monako, meskipun tanggung jawab pemerintah (tingkat negara) dan dari munisipalitas (tingkat kota) berbeda.[43] Berdasarkan konstituti pada tahun 1911, Monako dibagi menjadi tiga munisipalitas:[54]

- Monaco-Ville, kota tua di tanjung berbatu yang memanjang ke Laut Tengah, dikenal sebagai Batu Monako, atau hanya "The Rock";
- Monte Carlo, kawasan perumahan pokok dan resor dengan Kasino Monte Carlo di timur dan timur laut;
- La Condamine, bagian barat daya, termasuk daerah pelabuhan, Pelabuhan Hercules.

Munisipalitas itu digabung menjadi satu pada tahun 1917, setelah tuduhan bahwa pemerintah bertindak sesuai dengan motto "membagi dan menaklukkan" dan mereka diberikan status sebagai *ward* atau *quartiers*.

- Fontvieille, ditambahkan sebagai ward keempat, daerah yang baru dibangun dari reklamasi tanah pada tahun 1970-an;
- Moneghetti, menjadi ward kelima, dibuat dari sebagian La Condamine;
- Larvotto, menjadi ward keenam, dibuat dari sebagian Monte Carlo;
- La Rousse/Saint Roman (termasuk Le Ténao), menjadi ward ketujuh, juga dibuat dari sebagian Monte Carlo.

Di depan adalah La Condamine, ke kanan dengan pelabuhan kecil Fontvieille, dengan "Batu" (kota tua, benteng, dan istana) yang menonjol keluar antara dua pelabuhan, ke kiri dengan bangunan bertingkat tinggi La Rousse/Saint Roman.

Selanjutnya, ada tiga ward tambahan dibuat:

- Saint Michel, dibuat dari sebagian Monte Carlo;
- La Colle, dibuat dari sebagian dari La Condamine;
- Les Révoires, juga dibuat dari sebagian dari La Condamine.

Sebuah ward tambahan direncanakan akan direklamasi dari lahan baru yang diselesaikan awal tahun 2014;[55] tetapi Pangeran Albert II mengumumkan dalam pidato tahun baru 2009 bahwa ia telah mengakhiri rencana karena iklim ekonomi saat itu.[56] Namun, Pangeran Albert II pada pertengahan 2010 dengan tegas memulai kembali program tersebut.[57][58]

Quartier tradisional dan area geografis baru

Keempat *quartiers* tradisional Monako adalah: Monaco-Ville, La Condamine, Monte Carlo dan Fontvieille.[59][60] Namun, Moneghetti, bagian tingkat tinggi dari La Condamine, umumnya dipandang sebagai *Quartier* efektif kelima dari Monako, yang memiliki suasana yang sangat berbeda dan topografi bila dibandingkan dengan La Condamine.[61]

Ward

Saat ini Monako dibagi menjadi sepuluh *Ward*, dengan angka resmi mereka, baik Fontvieille II atau Le Portier, akan menjadi ward efektif yang kesebelas, jika dibangun:[58][62][63]

No.	Ward	Area (km²)	Populasi (Sensus tahun 2008)	Kepadatan (km²)	Blok Kota *(îlots)*	Keterangan
Bekas munisipalitas Monaco						
05	Monaco-Ville	0.19	1,034	5597	19	Kota Tua
Bekas munisipalitas Monte Carlo						
01	Monte Carlo/Spélugues (*Bd. Des Moulins-Av. de la Madone*)	0.30	3,834	10779	20	Area resor dan kasino
02	La Rousse/Saint Roman (*Annonciade-Château Périgord*)	0.13	3,223	30633	17	daerah timur laut, termasuk Le Ténao
03	Larvotto/Bas Moulins (*Larvotto-Bd Psse Grace*)	0.34	5,443	16570	17	Area pantai timur
10	Saint Michel (*Psse Charlotte-Park Palace*)	0.16	3,907	26768	24	Area permukiman tengah
Bekas munisipalitas La Condamine						
04	La Condamine	0.28	3,947	16213	28	Area pelabuhan barat laut
07	La Colle (*Plati-Pasteur-Bd Charles III*)	0.11	2,829	15005	15	Di perbatasan barat dengan Cap d'Ail
08	Les Révoires (*Hector Otto-Honoré Labande*)	0.09	2,545	33203	11	Teramasuk Jardin Exotique de Monaco
09	Moneghetti/ Bd de Belgique (*Bd Rainier III-Bd de Belgique*)	0.10	3,003	28051	17	Area permukiman tengah-utara
Tanah yang baru direklaim dari laut						
06	Fontvieille	0.35	3,901	10156	10	Mulai 1981
11 (1)	Fontvieille II	0.08 (1)	–	-	6 (1)	Pembangunan akan dimulai pada 2013[62]
11 (1)	Le Portier	0.05 (1)	–	-	4 (1)	Proyek diluncurkan kembali pada tahun 2012[64]
10	Monako[13][65]	2.05	35,352	16217	178	
(1) Tidak termasuk dalam total, karena hanya diusulkan						

Catatan: untuk keperluan statistik, Ward di Monako kemudian dibagi lagi menjadi 178 blok kota (îlots), yang sebanding dengan blok sensus di Amerika Serikat.[13]

Keamanan

Lihat pula: Penegakan hukum di Monako dan Militer Monako

Pengawal istana di Monako

Pertahanan bangsa yang lebih luas disediakan oleh Prancis. Monako tidak memiliki angkatan laut atau angkatan udara, tetapi pada kedua basis per-kapita dan per-area, Monako memiliki kepolisian terbesar (515 petugas polisi untuk 35.000 orang) dan kehadiran polisi di dunia.[66]

Ada juga kekuatan militer yang kecil yang terdiri dari unit pengawal pribadi pangeran dan istana di Monako-Ville yang disebut Compagnie des Carabiniers du Prince (Perusahaan Carabiniers Pangeran), yang dilengkapi dengan senjata modern seperti senapan M16A2 dan pistol 9 mm (Glock 17),[67] dan semua yang bersama-sama dengan korps militer, senjata api dan pertahanan sipil (pemadam kebakaran) membentuk sejumlah pasukan publik Monako.[68] *Compagnie des Carabiniers du Prince* diciptakan oleh Pangeran Honoré IV pada tahun 1817 untuk melindungi kerajaan dan keluarga pangeran. Perusahaan tersebut memiliki jumlah 116 perwira dan laki-laki, sedangkan perwira dan tentara bersifat lokal, petugas umumnya melayani di Tentara Prancis. Selain tugas menjaga mereka seperti yang dijelaskan, Carabiniers juga mematroli pantai kerajaan dan perairan pesisir.

Bendera

Artikel utama: Bendera Monako

Bendera Monako adalah salah satu desain bendera nasional tertua di dunia. Bendera Monako identik dengan Bendera Indonesia, kecuali untuk rasio tinggi dan lebar.[69]

Ekonomi

Artikel utama: Ekonomi Monako

Fontvieille dan pelabuhan yang baru.

Salah satu sumber utama penghasilan Monako adalah pariwisata. Setiap tahun banyak wisatawan tertarik dengan kasinonya (dengan pengecualian warga negara Monako boleh masuk kasino tetapi dilarang ikut berjudi) dan iklim yang nyaman. Pada tahun 2001, sebuah proyek konstruksi baru yang besar memperpanjang dermaga yang digunakan oleh kapal-kapal pesiar di pelabuhan utama. Monako telah berhasil mendiversifikasi basis ekonomi dalam layanan dan kecil, nilai tambah tinggi, industri non-polusi, seperti kosmetik dan biotermik.

Monako mempertahankan monopoli di berbagai sektor, termasuk tembakau dan layanan pos. Jaringan telepon (Monako Telecom) digunakan untuk dimiliki sepenuhnya oleh negara; sekarang hanya memiliki 45%, sedangkan 55% sisanya dimiliki oleh Cable & Wireless Communications (49%) dan Compagnie Monégasque de Banque (6%). Hal ini masih, bagaimanapun, monopoli. Standar hidup di Monako tinggi, kira-kira sebanding dengan di wilayah metropolitan Prancis.[70]

Monaco bukan anggota Uni Eropa, tetapi memiliki hubungan diplomatik dengan Uni Eropa serta menggunakan Euro sebagai mata uang resmi.

Transportasi

Artikel utama: Transportasi di Monako
Informasi lebih lanjut: Transportasi rel di Monako

Stasiun Monaco-Monte Carlo dilayani oleh SNCF, sistem rel nasional Prancis. Heliport Monako menyediakan pelayanan helikopter ke bandar udara terdekat, Bandar Udara Côte d'Azur di Nice, Prancis.

Panorama di La Condamine, Monako

Demografi

Artikel utama: Demografi Monako

Matahari terbenam di Monte Carlo.

Populasi Monako tidak biasa bahwa orang asli Monegasque adalah minoritas di negara mereka sendiri yang terdiri dari 21,6% dari populasi Monako. Kelompok terbesar adalah warga negara Prancis 28,4%, diikuti oleh Monegasque (21,6%), Italia (18,7%), Inggris (7,5%), Belgia (2,8%), Jerman (2,5%), Swiss (2,5%) dan warga negara Amerika Serikat (1,2%).[71]

Warga naturalisasi Monako disebut *Monacans*, sedangkan *Monegasque* merupakan istilah yang tepat untuk menggambarkan seseorang yang lahir di Monako.[72]

Bahasa

Artikel utama: Bahasa di Monako

Bahasa resmi Monako adalah Prancis, sedangkan Italia dituturkan oleh komunitas Italia yang cukup besar. Inggris digunakan oleh orang Amerika, Inggris, Kanada, dan Irlandia. Bahasa nasional Monégasque, sekarang dituturkan oleh hanya sebagian kecil penduduk. Bahasa ini menyerupai Liguria, yang diucapkan di Genoa. Di Monaco-Ville, tanda-tanda jalan yang dicetak dalam bahasa Prancis dan Monégasque.[73][74]

Agama

Agama di Monako (2012)[75][note 2]	
Katolik	83,2%
Tidak beragama	12,9%
Yahudi	2,9%
Islam	0,8%
Lainnya	0,5%

Katolik Roma

Artikel utama: Katolik Roma di Monako

Katedral Santo Nicholas, Monako

Agama resmi Monako adalah Katolik, dengan kebebasan beragama lain yang dijamin oleh konstitusi.[75] Ada lima gereja paroki Katolik Roma di Monako dan satu Katedral, yang merupakan tempat kedudukan uskup agung di Monako. Keuskupan, yang telah ada sejak pertengahan abad ke-19, diangkat ke keuskupan agung pada tahun 1981 sebagai Keuskupan Agung Monako. Santo Pelindung Monako adalah Santo Devota.

Katolik dianut oleh 83,2% penduduk Monako.[75]

Anglikan

Ada satu gereja Anglikan, gereja St. Paul, yang terletak di Avenue de Grande Bretagne di Monte Carlo. Pada tahun 2007 gereja ini memiliki keanggotaan formal dari 135 penduduk Anglikan di Monako, tetapi juga melayani sejumlah anggota yang jauh lebih besar dari penganut Anglikan sementara di dalam negeri, sebagian besar sebagai wisatawan. Situs gereja juga mengakomodasi perpustakaan bahasa Inggris lebih dari 3.000 buku.[76] Gereja ini adalah bagian dari Keuskupan Eropa Anglikan.

Yahudi

Asosiasi *Culturelle Israélite de Monaco* (didirikan 1948) adalah rumah konversi yang berisi sebuah sinagoge, sebuah sekolah komunitas Ibrani, dan toko makanan halal, yang terletak di Monte Carlo.[77] Komunitas ini (sekitar 1.000) terutama terdiri dari orang-orang pensiunan Yahudi dari Inggris (40%) dan Afrika Utara.[78] Dua pertiga dari penduduk Yahudi adalah Sephardi, terutama dari Afrika Utara, sementara sepertiga lainnya adalah Ashkenazi.[79]

Pendidikan

Sekolah Dasar dan Menengah

Monaco memiliki sepuluh sekolah yang diatur negara, termasuk: tujuh taman kanak-kanak dan sekolah dasar; satu sekolah menengah, *Collège Charles III*;[80] satu *lycée* yang menyediakan pelatiahn umum dan teknologi, *Lycée Albert 1er*;[81] dan satu lycée yang menyediakan pelatihan kejuruan dan hotel, *Lycée technique et hôtelier de Monte-Carlo*.[82] Ada juga dua sekolah hibah yang dibantu denominasi swasta, termasuk *Institution François d'Assise Nicolas Barré* dan *École des Sœurs Dominicaines*, dan satu sekolah internasional, *International School of Monaco*.[83]

Universitas

Ada satu universitas yang terletak di Monako, yaitu Universitas Internasional Monako (*International University of Monaco*), sebuah sekolah berbahasa Inggris yang mengkhususkan diri dalam pendidikan bisnis dan dioperasikan oleh kelompok sekolah *Institut des hautes études économiques et commerciales* (INSEEC).

Budaya

Artikel utama: Budaya Monako

Musik

Seaside façade of the Salle Garnier, rumah dari festival Opéra de Monte-Carlo

Monaco memiliki gedung opera, orkestra simfoni, dan perusahaan balet klasik.[84]

Seni visual

Monako memiliki museum nasional seni visual kontemporer di Museum Nasional Baru Monako. Negara ini juga memiliki banyak karya seni publik, patung, museum, dan peringatan.

Museum di Monako

Oceanographic Museum

Ada beberapa museum di Monako, diantaranya:

1. Koleksi Mobil Top Monaco
2. Museum Napoleon (Monako)
3. Museum Oseanografi

Acara, festival, dan pertunjukan

Principality of Monaco menyelenggarakan acara internasional besar seperti:

- Festival Sirkus Internasional Monte-Carlo
- Mondial du Théâtre
- Festival Televisi Monte Carlo

Lihat pula

- Hubungan luar negeri Monako
- Daftar penguasa Monako
- Musik Monako
- Garis Besar Monaco
- Telekomunikasi Monaco

Catatan

1. Informasi lebih lanjut lihat Bahasa di Monako.
2. Persentase berdasarkan pada populasi 35.000 orang.

Referensi

1. "Population on 1 January and is one of the smallest country. It is 2nd most smallest country". *ec.europa.eu/eurostat*. Eurostat. Diarsipkan dari versi asli tanggal 5 February 2020. Diakses tanggal 4 February 2020.
2. "Recensement de la Population 2016" (PDF) (dalam bahasa Prancis). Institut Monégasque de la Statistique et des Études Économiques (IMSEE). February 2018. Diarsipkan dari versi asli (PDF) tanggal 24 February 2020. Diakses tanggal 10 February 2020.
3. "EUROPE :: MONACO". *CIA.gov*. Central Intelligence Agency. Diarsipkan dari versi asli tanggal 30 December 2021. Diakses tanggal 4 February 2020.
4. "GDP (current US$) - Monaco". *data.worldbank.org*. World Bank. Diarsipkan dari versi asli tanggal 14 March 2019. Diakses tanggal 25 January 2022.
5. "GDP per capita (current US$) - Monaco". *data.worldbank.org*. World Bank. Diarsipkan dari versi asli tanggal 3 February 2020. Diakses tanggal 25 January 2022.
6. Quality of Life, Balance of Powers, and Nuclear Weapons (https://books.google.com/books?id=p--IYwyuog0C&pg=PA51&#v=onepage&q&f=false) Avakov, Aleksandr Vladimirovich. Algora Publishing, 27 Jan 2012.
7. "HowStuffWorks "Geography of Monaco" ". Geography.howstuffworks.com. 30 March 2008. Diarsipkan dari versi asli tanggal 2013-09-02. Diakses tanggal 22 March 2012.
8. Monaco Statistical Data of 2017 (http://www.monacostatistics.mc/IMSEE/Publications/monaco-statistics-pocket).
9. "CIA - The World Factbook". Cia.gov. Diarsipkan dari versi asli tanggal 2010-07-11. Diakses tanggal 22 March 2012.
10. "Geography and Map of Monaco". Geography.about.com. Diarsipkan dari versi asli tanggal 2013-05-11. Diakses tanggal 22 March 2012.
11. "Monaco - Monaco's Areas / Geography / About Monaco / Monaco Official Site". Visitmonaco.com. Diakses tanggal 2013-03-12.
12. "cheminsanciensturbie". Archeo-alpi-maritimi.com. Diakses tanggal 22 March 2012.
13. "Plan Général de la Principauté de Monaco" (PDF). Diarsipkan dari versi asli (PDF) tanggal 2012-05-28. Diakses tanggal 28 May 2012.
14. Samuel, Henry (28 December 2009). "Monaco to build into the sea to create more space". London: Telegraph. Diakses tanggal 22 March 2012.
15. Robert BOUHNIK (19 October 2010). "Home > Files and Reports > Public works(Gb)". Cloud.gouv.mc. Diarsipkan dari versi asli tanggal 2012-12-20. Diakses tanggal 22 March 2012.
16. "Royal Opinions - Social, Political, & Economical Affairs of Monaco". Royalopinions.proboards.com. Diarsipkan dari versi asli tanggal 2012-11-27. Diakses tanggal 22 March 2012.
17. Robert BOUHNIK (19 October 2010). "Home > Files and Reports > Public works > 2002 Archives — Extension of "La Condamine Port"(Gb)". Cloud.gouv.mc. Diakses tanggal 22 March 2012.
18. "Monaco remet sur le tapis le projet d'extension en mer". Econostrum.info. Diakses tanggal 22 March 2012.
19. "Monaco". State.gov. 16 November 2011. Diakses tanggal 22 March 2012.
20. "Monaco Politics - the unusual political system of Monaco". Nice-city-vacation.com. Diarsipkan dari versi asli tanggal 2013-02-24. Diakses tanggal 22 March 2012.
21. Faktanya Francesco Grimaldi, yang menangkap the Rock pada malam 8 Januari 1297, terpaksa melarikan diri Monako hanya empat tahun setelah serangan yang dibuat-buat, tidak pernah kembali. Grimaldi tidak dapat secara permanen mengamankan pegangan mereka sampai 1419 ketika mereka membeli Monako, bersama dengan dua desa tetangganya, Menton dan Roquebrune. Source: Edwards, Anne (1992). *The Grimaldis of Monaco: The Centuries of Scandal - The Years of Grace*. William Morrow. ISBN 978-0-688-08837-8.

22. "Monaco Military 2012, CIA World Factbook". Theodora.com. Diakses tanggal 28 May 2012.
23. "Google Translate". Translate.googleusercontent.com. Diakses tanggal 22 March 2012.
24. "Compagnie des Carabiniers du Prince / Département de l'Intérieur / Le Gouvernement / Gouvernement et Institutions / Portail du Gouvernement - Monaco" (dalam bahasa (Prancis)). Gouv.mc. Diakses tanggal 2013-03-12.
25. "Monaco - Economy and Trade of Monaco". Qfinance. Diarsipkan dari versi asli tanggal 2013-05-08. Diakses tanggal 22 March 2012.
26. "Monaco: Economy >> globalEDGE: Your source for Global Business Knowledge". Globaledge.msu.edu. Diakses tanggal 22 March 2012.
27. Robert BOUHNIK (19 December 2011). "Home > Files and Reports > Economy(Gb)". Cloud.gouv.mc. Diarsipkan dari versi asli tanggal 2012-07-11. Diakses tanggal 22 March 2012.
28. "Monaco Economy 2012, CIA World Factbook". Theodora.com. Diakses tanggal 28 May 2012.
29. μόνος (https://web.archive.org/web/20110629164313/http://www.perseus.tufts.edu/hopper/text?doc=Perseus%3Atext%3A1999.04.0057%3Aentry%3Dmo%2Fnos), Henry George Liddell, Robert Scott, *A Greek-English Lexicon*, on Perseus Digital Library
30. οἶκος (https://web.archive.org/web/20110629164225/http://www.perseus.tufts.edu/hopper/text?doc=Perseus%3Atext%3A1999.04.0057%3Aentry%3Doi%29%3Dkos1), Henry George Liddell, Robert Scott, *A Greek-English Lexicon*, on Perseus Digital Library
31. "History of Monaco". Monaco-montecarlo.com. Diakses tanggal 28 May 2012.
32. *Strabo, Geography, Gaul, 4.6.3* at LacusCurtious (http://penelope.uchicago.edu/Thayer/E/Roman/Texts/Strabo/4F*.html)
33. μόνοικος (https://web.archive.org/web/20110629164248/http://www.perseus.tufts.edu/hopper/text?doc=Perseus%3Atext%3A1999.04.0057%3Aentry%3Dmo%2Fnoikos), Henry George Liddell, Robert Scott, *A Greek-English Lexicon*, on Perseus Digital Library
34. "Monaco". State.gov. 16 November 2011. Diakses tanggal 28 May 2012.
35. "Monaco Life". Monaco Life. 26 July 2011. Diakses tanggal 28 May 2012.
36. "Monaco history". Visitmonaco.com. Diakses tanggal 28 May 2012.
37. "Monaco - The Principality of Monaco". Monaco.me. Diakses tanggal 28 May 2012.
38. "Monaco Districts | Monaco". Monaco.me. Diakses tanggal 22 March 2012.
39. "Monaco: City Guide, weather and facts galore from". Answers.com. Diakses tanggal 6 September 2012.
40. "Highest and lowest points in countries islands oceans of the world". Worldatlas.com. Diakses tanggal 6 September 2012.
41. "Climatological information for Monaco" (http://www.visitmonaco.com/fr/Monaco-Pratique/Climat) – Monaco website
42. "Politics". Monaco-IQ. Diakses tanggal 28 May 2012.
43. "History « Consulate General of Monaco". Monaco-consulate.com. Diarsipkan dari versi asli tanggal 2012-06-10. Diakses tanggal 28 May 2012.
44. "Monaco: Government >> globalEDGE: Your source for Global Business Knowledge". Globaledge.msu.edu. 4 October 2004. Diakses tanggal 28 May 2012.
45. "Monaco". Freedom House. Diarsipkan dari versi asli tanggal 2012-11-15. Diakses tanggal 28 May 2012.
46. "Deux listes pour une mairie". Diarsipkan dari versi asli tanggal 2013-05-10. Diakses tanggal 2013-05-17.
47. "Les Élus". Diarsipkan dari versi asli tanggal 2013-05-15. Diakses tanggal 2013-05-17.
48. "La Mairie > Le Conseil Communal". Diarsipkan dari versi asli tanggal 2013-01-16. Diakses tanggal 2013-05-17.
49. Élections communales à Monaco: vingt-quatre candidats en lice (http://www.nicematin.com/article/actualites/elections-communales-a-monaco-vingt-quatre-candidats-en-lice.460784.html)
50. Robertson, Alex (1 February 2012). "The 10 smallest countries in the world". Gadling.com. Diakses tanggal 28 May 2012.
51. "Marinas, Ports & Anchorages in Monaco". Worldmarineguide.com. Diakses tanggal 28 May 2012.
52. "Population Density". Geography.about.com. Diarsipkan dari versi asli tanggal 2017-02-01. Diakses tanggal 28 May 2012.
53. "Is Monaco a city-state of a country". Wiki.answers.com. Diakses tanggal 28 May 2012.
54. "About Monaco". JCI EC 2013. 3 March 2010. Diarsipkan dari versi asli tanggal 2014-01-15. Diakses tanggal 28 May 2012.
55. "West 8 Urban Design & Landscape Architecture / projects / Cape Grace, Monaco". West8.nl. Diarsipkan dari versi asli tanggal 2017-06-30. Diakses tanggal 28 May 2012.
56. "The new Monaco skyline". CityOut Monaco. 17 March 2010. Diarsipkan dari versi asli tanggal 2011-10-11. Diakses tanggal 28 May 2012.
57. Samuel, Henry (28 December 2009). "Monaco to build into the sea to create more space". London: Telegraph. Diakses tanggal 28 May 2012.
58. "Prince speaks of future developments". CityOut Monaco. 29 December 2009. Diarsipkan dari versi asli tanggal 2011-10-11. Diakses tanggal 28 May 2012.
59. "Monaco - Location and size, Population, Agriculture, Tourism, International trade, Working conditions". Nationsencyclopedia.com. 2 July 2011. Diakses tanggal 28 May 2012.
60. "Dictionary - Definition of Larvotto". Websters-online-dictionary.org. 1 March 2008. Diakses tanggal 28 May 2012.
61. "Tourist Board official website". Visitmonaco.com. Diakses tanggal 28 May 2012.
62. Nom (obligatoire). "Extension en mer : Fontvieille ou Larvotto ? | Monaco Hebdo". Monacohebdo.mc. Diarsipkan dari versi asli tanggal 2015-10-16. Diakses tanggal 2013-03-12.
63. "Monaco Commune". Statoids.com. Diakses tanggal 28 May 2012.
64. "Monaco: une extension en mer au Larvotto de nouveau à l'étude". Nice-Matin. 2012-06-13. Diakses tanggal 2013-03-12.
65. "Monaco Statistiques Pocket / Publications / Analyses et Statistiques / L'Économie / Action Gouvernementale / Portail du Gouvernement - Monaco" (dalam bahasa (Prancis)). Gouv.mc. Diakses tanggal 6 September 2012.
66. "Division de Police Maritime et Aéroportuaire / Direction de la Sûreté Publique / Département de l'Intérieur / Le Gouvernement / Gouvernement et Institutions / Portail du Gouvernement - Monaco" (dalam bahasa (Prancis)). Gouv.mc. 16 August 1960. Diakses tanggal 28 May 2012.
67. "The Palace Guards - Prince's Palace of Monaco". Palais.mc. 27 January 2011. Diarsipkan dari versi asli tanggal 2012-04-23. Diakses tanggal 28 May 2012.
68. "Salinan arsip". Diarsipkan dari versi asli tanggal 2013-12-06. Diakses tanggal 2013-05-17.
69. "Monaco Flag – World Flags 101 – Monacan Flags". Worldflags101.com. Diakses tanggal 2 July 2011.
70. "CIA - The World Factbook". Cia.gov. Diarsipkan dari versi asli tanggal 2010-07-11. Diakses tanggal 28 May 2012.
71. "General Population Census 2008: Population Recensée et Population Estimée" (PDF) (dalam bahasa French). Government of the Principality of Monaco. 2008. Diarsipkan dari versi asli (PDF) tanggal 2011-06-14. Diakses tanggal 7 October 2011.
72. "Culture of Monaco - history, people, clothing, traditions, women, beliefs, food, customs, family". Everyculture.com. Diakses tanggal 6 September 2012.
73. "Society". Monaco-IQ. Diakses tanggal 6 September 2012.
74. "Principality of Monaco - Monaco Monte-Carlo". Monte-carlo.mc. Diakses tanggal 6 September 2012.
75. Joshua Project. "Ethnic People Groups of Monaco". Joshua Project. Diakses tanggal 2013-03-12.
76. St Paul's Church, Monaco (http://www.stpaulsmonaco.com/)
77. "Synagogues in Monte Carlo - Shuls in Monte Carlo - Jewish Temples in Monte Carlo". Mavensearch.com. 6 July 2007. Diakses tanggal 28 May 2012.
78. "Jews statistics - countries compared". NationMaster. Diakses tanggal 28 May 2012.
79. Details at Jewish Virtual Library (http://www.jewishvirtuallibrary.org/jsource/vjw/monaco.html)
80. "Collège Charles III". College-charles3.mc. Diarsipkan dari versi asli tanggal 2011-05-11. Diakses tanggal 28 August 2010.
81. "Lycée Albert 1er". Lycee-albert1er.mc. Diarsipkan dari versi asli tanggal 2011-07-22. Diakses tanggal 28 August 2010.
82. "Lycée technique et hôtelier de Monte-Carlo" (dalam bahasa French). Monaco. Diarsipkan dari versi asli tanggal 2011-07-22. Diakses tanggal 23 May 2009.
83. "Education System". Diakses tanggal 15 February 2013.
84. "Culture of Monaco". *everyculture.com*.

Pranala luar

Pemerintah

- Official Government Portal (http://www.gouv.mc/)
- Official website of the Prince's Palace of Monaco (http://www.palais.mc/)
- Chief of State and Cabinet Members (https://www.cia.gov/library/publications/world-leaders-1/world-leaders-m/monaco.html) Diarsipkan (https://web.archive.org/web/20111108162611/https://www.cia.gov/library/publications/world-leaders-1/world-leaders-m/monaco.html) 2011-11-08 di Wayback Machine.

Informasi Umum

- Monaco (https://www.cia.gov/library/publications/the-world-factbook/geos/mn.html) di *CIA World Factbook*.
- Monaco (http://ucblibraries.colorado.edu/govpubs/for/monaco.htm) Diarsipkan (https://web.archive.org/web/20080607085244/http://ucblibraries.colorado.edu/govpubs/for/monaco.htm) 2008-06-07 di Wayback Machine. dari *UCB Libraries GovPubs*
- Monako (https://curlie.org/Regional/Europe/Monaco) di Curlie (dari DMOZ)
- Monaco (https://www.bbc.co.uk/news/world-europe-17615784) dari BBC News
- Monaco (http://www.monaco.me/) informasi tentang Monako
- History of Monaco: Primary documents (http://eudocs.lib.byu.edu/index.php/History_of_Monaco:_Primary_Documents)
-
- Peta Monaco di Wikimedia Atlas
-
- OpenStreetMap memiliki data geografis tentang Monako (https://www.openstreetmap.org/browse/relation/1124039)

Pariwisata

- Official website for Tourism (http://www.visitmonaco.com/)
- Your Monaco (http://www.yourmonaco.com/) Panduan wisata Monako
- Principality Monaco (http://www.principality-monaco.com/) Wisata Monako dan situs penawaran khusus
- MonacoWeb.com (http://www.monacoweb.com/) Portal interaktif untuk daftar real estate, acara & hiburan, dan iklan gratis
- Discovery of Monaco (http://www.petitmonegasque.fr/)
- maBoum.com (http://maboum.com/) Panduan tak resmi untuk apa yang terjadi di Monako
- A selection of 30 very representative photos of Monaco (http://www.jmpatin.fr/myPictures/?q=album/36-monaco)
- map of Monaco (http://mapofeurope.com/monaco)

Pekerjaan

- Monaco Job Portal (http://www.work-monaco.com/) Diarsipkan (https://web.archive.org/web/20111016171119/http://www.work-monaco.com/) 2011-10-16 di Wayback Machine.

Lain-lain

- Order of the doctors of Monaco (http://www.ordremedecins.mc/) **(Prancis)**
- French Monaco Web portail (http://www.monaco-prestige.info/) **(Prancis)**
- La Principauté – Le premier journal d'actualité de Monaco (http://glomed.free.fr/laprincipauté.html/)
- *Monaco Today*, sebuah surat kabar dalam Bahasa Inggris, Monacolife.net (http://www.monacolife.net/)
- Monacolife.net (http://www.monacolife.net/) Portal berita berbahasa Inggris
- The Monaco Times (http://www.monacotimes.com/)
- Monaco-IQ (http://www.monaco-iq.com/) Informasi tentang Monako dan agregator berita
- Monte-Carlo (http://www.ilprincipato.com/) Diarsipkan (https://web.archive.org/web/20111030113437/http://www.ilprincipato.com/) 2011-10-30 di Wayback Machine. Portal tak resmi Monte-Carlo Italia

---

Diperoleh dari "https://id.wikipedia.org/w/index.php?title=Monako&oldid=24248282"